Ekaya Explore

Membros:

- Sheldon Jasse
- Kelvin Loforte
- Tiago Antunes

Porto, 2026/2027

Indíce

1. Introdução..... 4

1.1. Contexto..... 4

1.2. Objetivo do projeto..... 4

1.3. Visão geral da solução..... 4

2. Problema e Oportunidade..... 5

2.1. Problema atual no turismo..... 5

2.2. Oportunidade..... 5

2.3. O que aprendemos com o questionário / entrevistas.....6

3. Ideia Central da Solução..... 7

3.1. Conceito principal..... 7

3.2. Utilizador-alvo..... 7

3.3. Proposta de valor..... 7

4. Funcionalidades Principais..... 8

4.1. Roteiros inteligentes..... 9

4.2. “Story Stops”..... 9

4.3. Gamificação e sistema de pontos..... 9

4.4. Modo offline-first..... 9

5. Protótipo e Interface..... 10

5.1. Ferramenta usada..... 10

5.2. Principais ecrãs..... 10

5.3. Fluxo de utilização..... 11

6. Impacto Esperado..... 12

6.1. Para turistas..... 12

6.2. Para comunidades e pequenos negócios..... 12

6.3. Indicadores simples de sucesso..... 12

7. Riscos e Limitações..... 13

8. Próximos Passos..... 14

8.1. Teste piloto (ex.: Ilha de Moçambique)..... 14
8.2. Melhorias a partir do feedback..... 14
8.3. Possível expansão para outros destinos..... 14

9. Conclusão..... 15

Introdução

Moçambique é um país com um enorme potencial turístico, graças às suas praias, ilhas, parques naturais, diversidade cultural e riqueza histórica. No entanto, muitos visitantes acabam por conhecer apenas uma parte "superficial" do país, concentrando-se em poucos destinos mais conhecidos e em serviços formais, enquanto grande parte das comunidades e experiências autênticas permanece invisível. Esta realidade é agravada por desafios como a falta de informação organizada no local e as limitações de conectividade à internet, sobretudo fora dos grandes centros urbanos.

Perante este cenário, o nosso grupo decidiu desenvolver uma solução focada em turismo que responda diretamente a estes desafios. O objetivo central do projeto é criar uma plataforma que funcione como um "guia de bolso" inteligente, permitindo ao turista explorar Moçambique de forma mais autónoma, profunda e conectada com as comunidades locais, mesmo em contextos de internet limitada. Para isso, combinamos quatro pilares principais: roteiros estruturados, pontos de interesse com histórias locais ("Story Stops"), um sistema de gamificação que recompensa a exploração e um funcionamento offline-first pensado para a realidade moçambicana.

Este relatório apresenta, de forma clara e acessível, o contexto em que a ideia surgiu, o problema identificado, a solução proposta e o protótipo desenvolvido. O objetivo é tornar o projeto compreensível para qualquer leitor – desde professores e júris até potenciais parceiros – mostrando não só a parte tecnológica, mas também o impacto que esta solução pode ter no turismo, nas comunidades de Moçambique e na economia do próprio pais.

2. Problema e Oportunidade

2.1. Problema atual no turismo

Apesar do seu potencial, o turismo em Moçambique ainda é vivido de forma muito limitada por grande parte dos visitantes. Muitos turistas concentram-se em poucos pontos "famosos" e em experiências superficiais, sem aceder a outras regiões, histórias e serviços que o país tem para oferecer. Isto acontece, em grande parte, porque:

- Falta informação clara e organizada no próprio destino sobre o que visitar, como circular e que experiências autênticas existem.
- Pequenos negócios e comunidades locais têm pouca visibilidade digital, ficando fora dos principais canais usados por turistas (apps globais, grandes plataformas de reservas).
- Em muitas zonas, o acesso à internet é fraco, caro ou instável, o que torna difícil depender apenas de soluções online para orientar a viagem.

Como resultado, o turista sente-se menos autónomo, explora menos o país do que poderia, e uma parte relevante do dinheiro do turismo não chega às comunidades locais que poderiam beneficiar dele.

2.2. Oportunidade

Ao mesmo tempo, existe uma oportunidade clara:

- O turismo em Moçambique está a crescer e o interesse por destinos autênticos e menos massificados aumenta.
- Muitos viajantes, especialmente os mais independentes, procuram experiências ligadas à cultura local, contacto com comunidades e descoberta "para além do básico".
- As tecnologias atuais permitem criar soluções que funcionam mesmo com pouca internet, combinando conteúdos offline com atualizações pontuais quando há Wi-Fi.

Isto abre espaço para uma plataforma que:

- organize informação de forma simples e acessível,
- ligue turistas diretamente a experiências e negócios locais,
- e funcione bem em contexto de conectividade limitada.

É exatamente este espaço que o nosso projeto pretende ocupar, transformando o modo como Moçambique é descoberto e como o turismo se distribui pelo território.

2.3 O que aprendemos com o questionário / entrevistas

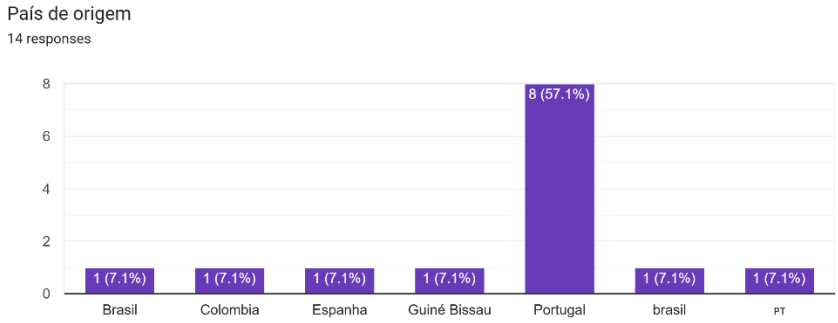

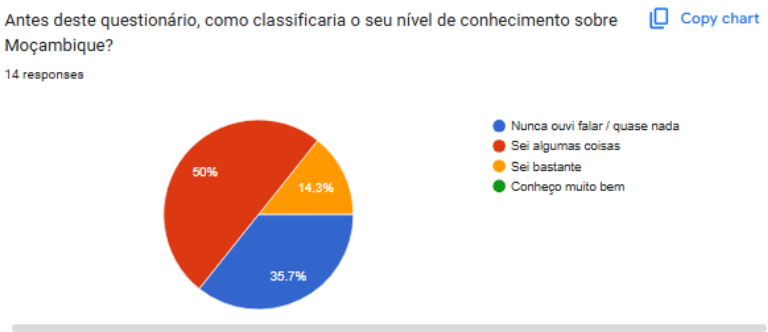

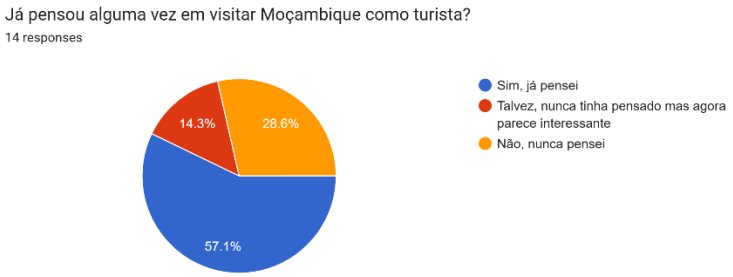

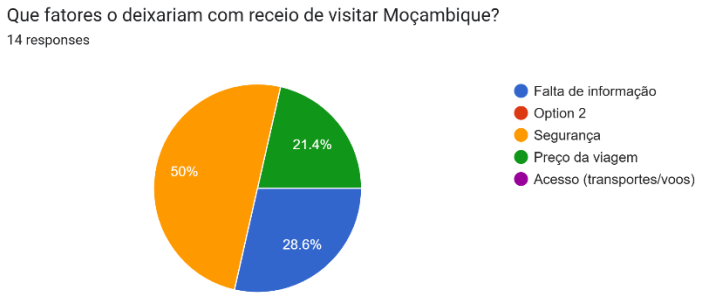

Pelas respostas do questionário, dá para aprender algumas coisas importantes:

1. **Conhecimento sobre Moçambique é limitado, mas existe curiosidade**
    - Metade dos participantes respondeu que "sei algumas coisas" sobre Moçambique, e mais de um terço "quase nada".
    - Mesmo assim, 57,1% já tinham pensado em visitar o país, e quase 30% passaram a achar interessante depois da pergunta.
      → Ou seja: Moçambique não é muito conhecido em detalhe, mas tem potencial de interesse se for melhor apresentado.
2. **Principais motivos para visitar**
    - Os motivos mais escolhidos foram "praias e natureza" (38,5%) e "vida selvagem/safaris" (30,8%), seguidos de "cultura e história".
      → Isso confirma que a imagem mais forte do país está ligada à natureza e safaris, e a nossa plataforma pode ajudar a ligar isso a conteúdos culturais e comunitários, que hoje quase não aparecem.
3. **Principais receios em visitar Moçambique**
    - A maior fatia do gráfico de receios (50%) está ligada a preço da viagem, seguida de falta de informação (28,6%) e segurança.
      → O nosso projeto ataca diretamente a parte da falta de informação, ajudando o turista a sentir-se mais seguro e preparado com roteiros, mapas e histórias locais.
4. **Onde as pessoas procuram informação antes de viajar**
    - As respostas mostram peso forte em Google/motores de busca e redes sociais, seguidos de apps de viagem e sites oficiais.
      → Isto mostra que, se a nossa solução crescer, faz sentido pensar em estar bem posicionado online (SEO, redes sociais), mas também reforça a importância de um guia dedicado que organize melhor a informação sobre Moçambique.

3. Ideia Central da Solução

A nossa solução é uma plataforma de turismo offline-first que funciona como um guia de bolso inteligente para destinos em Moçambique. Em vez de o turista depender apenas de pesquisas na internet ou de informação limitada no local, passa a ter num só sítio mapas, roteiros sugeridos e pontos de interesse com

histórias de comunidades locais ("Story Stops"), que pode descarregar quando tem Wi-Fi e usar depois sem ligação à internet.

O foco está em dois tipos de utilizador:

- o turista independente (nacional ou estrangeiro) que quer explorar para além do básico, com mais autonomia e segurança;
- as comunidades e pequenos negócios locais, que ganham um espaço dedicado para apresentar as suas experiências, serviços e histórias a quem visita o destino.

O que torna a nossa solução diferente é a combinação de três pilares:

- Roteiros inteligentes, organizados por duração (1 dia, 3 dias, 7 dias) e por tema (praias, cultura, comunidade), que guiam o utilizador passo a passo;
- Story Stops, que transformam cada ponto do mapa numa oportunidade de conhecer melhor o lugar, através de descrições, imagens e contactos de pessoas reais;
- Gamificação e sistema de pontos, que recompensa o utilizador sempre que segue um roteiro, visita um ponto ou participa numa experiência local, incentivando-o a explorar mais e a interagir com o destino.

Assim, a plataforma não é apenas um mapa ou um catálogo de atrações: é uma forma de ligar turistas e comunidades, adaptada à realidade de conectividade limitada de Moçambique e pensada para gerar mais conhecimento sobre o país e mais impacto direto na economia local.

4. Funcionalidades Principais

4.1. Roteiros inteligentes

A plataforma oferece **roteiros organizados por duração e tema**, para orientar o turista de forma simples:

- Roteiros de 1 dia, 3 dias e 7 dias.
- Roteiros temáticos, como "Praias e Natureza", "Cultura e História" ou "Experiências Comunitárias".
  Cada roteiro indica a **sequência de paragens**, tempo médio em cada ponto, distância aproximada e dicas práticas (melhor horário, o que levar, nível de esforço). O objetivo é que qualquer pessoa consiga seguir o roteiro sem precisar de guia físico.

4.2. “Story Stops” – Pontos com histórias locais

Ao longo dos roteiros e do mapa, existem os **“Story Stops”**, que são pontos de interesse enriquecidos com conteúdo local:

- Pequenas histórias sobre o local (origem, curiosidades, tradições).
- Fotos e descrições simples do que o turista pode ver ou fazer ali.
- Informação sobre **quem está por detrás** (comunidades, guias, artesãos, negócios locais) e contactos básicos.
  Os Story Stops transformam o mapa num conjunto de “histórias vivas”, aproximando o turista das pessoas e não apenas dos lugares.

4.3. Sistema de gamificação e pontos

Para tornar a experiência mais envolvente, a plataforma integra um **sistema de gamificação**:

- O utilizador ganha **pontos** ao:
  - seguir um roteiro,
  - marcar um Story Stop como visitado,
  - participar numa experiência comunitária.
- Esses pontos permitem desbloquear **selos e níveis** (por exemplo: “Explorador de Praias”, “Amigo da Comunidade”), incentivando a explorar mais e a voltar a usar a aplicação.
  Este mecanismo ajuda a combater o turismo superficial, recompensando quem se interessa em conhecer o destino em maior profundidade.

4.4. Modo offline-first

A solução é pensada desde o início para funcionar **mesmo com internet limitada**:

- O utilizador descarrega, através de Wi-Fi (por exemplo no hotel), o **pacote do destino**: mapas simplificados, roteiros, Story Stops e informação essencial.
- Depois disso, pode usar a plataforma durante o dia **completamente offline**, vendo o mapa, consultando roteiros e registando visitas.
- Quando voltar a ter internet, os dados podem ser sincronizados (atualização de conteúdos, envio de estatísticas de uso, etc.).
  Isto garante que o turista não fica dependente de dados móveis caros ou instáveis para aproveitar a experiência.

5. Protótipo e Interface

5.1. Ferramentas e abordagem

O protótipo foi desenhado em Figma, com o objetivo de representar de forma simples e clara como o utilizador iria interagir com a plataforma. Mais do que mostrar todos os detalhes técnicos, o foco do protótipo é ilustrar o **fluxo de utilização**: como o turista entra, escolhe um destino, descarrega conteúdos e começa a explorar os roteiros e Story Stops.

5.2. Principais ecrãs do protótipo

No protótipo destacam-se alguns ecrãs centrais:

- **Ecrã inicial**
  Apresenta o nome da plataforma e um menu simples com as opções principais:
  - "Roteiros",
  - "Mapa",
  - "Experiências Locais",
  - "O meu Progresso" (pontos e conquistas).
- **Ecrã de lista de roteiros**
  Mostra os roteiros disponíveis, com indicação de:
  - duração (1 dia, 3 dias, 7 dias),
  - tema (praias, cultura, comunidade),
  - breve descrição.
    O utilizador seleciona um roteiro para ver o detalhe e começar a seguir.
- **Ecrã de detalhe de roteiro**
  Apresenta a sequência de paragens em formato de lista ou linha temporal, com:
  - nome de cada ponto,
  - pequena descrição,
  - tempo estimado,
  - botão para abrir no mapa.

- **Mapa com Story Stops**
  Um mapa simples com ícones diferentes para:
  - pontos de interesse geral,
  - experiências comunitárias,
  - locais incluídos no roteiro escolhido.
    Ao tocar num ícone, abre-se o cartão do Story Stop.
- **Ecrã de Story Stop**
  Cartão com:
  - nome do local,
  - foto,
  - história/descrição curta,
  - informação prática (horário, recomendações),
  - contacto do negócio/comunidade (se aplicável),
  - botão "Marcar como visitado" que alimenta o sistema de pontos.
- **Ecrã de gamificação / progresso**
  Mostra os pontos acumulados, selos conquistados e níveis do utilizador. A ideia é o turista conseguir ver de forma rápida o quanto já explorou do destino.

5.3. Fluxo de utilização demonstrado

O protótipo demonstra o seguinte fluxo básico:

1. O utilizador entra na plataforma e vê o ecrã inicial.
2. Escolhe um roteiro ou abre diretamente o mapa.
3. Consulta os detalhes do roteiro e começa a seguir as paragens sugeridas.
4. No mapa, abre Story Stops, lê as histórias e vê informações práticas.
5. Marca pontos como "visitados" e, com isso, acumula pontos e selos no ecrã de progresso.

Mesmo sendo um protótipo, este conjunto de ecrãs permite explicar visualmente **como a solução funciona na prática** e como ela apoia o turista na exploração do destino.

6. Impacto Esperado

6.1. Impacto para turistas

Espera-se que a plataforma torne **Moçambique mais fácil e seguro de explorar** para turistas independentes, mesmo com internet limitada. Com roteiros claros, Story Stops e informação prática reunida num só lugar, o utilizador ganha mais **autonomia** para organizar o seu dia, descobrir novos pontos de interesse e compreender melhor o contexto cultural de cada local. A gamificação ajuda a manter o interesse ao longo da viagem, incentivando a explorar mais do que apenas os sítios "óbvios".

6.2. Impacto para comunidades e pequenos negócios

Ao dar visibilidade a experiências comunitárias e a pequenos negócios locais, o projeto pretende **aproximar turistas e residentes**, facilitando o contacto direto e potencialmente aumentando a procura por serviços locais. Isso pode traduzir-se em **mais rendimento para as comunidades**, maior valorização do património imaterial (histórias, tradições, modos de vida) e incentivo à preservação de práticas culturais, já que passam a ser reconhecidas como parte da oferta turística.

6.3. Como saber se está a funcionar

De forma prática, a solução será considerada bem-sucedida se for possível observar, ao longo do tempo, sinais como:

- crescimento do número de utilizadores que descarregam e usam os roteiros;
- aumento de Story Stops marcados como visitados e de missões concluídas no sistema de pontos;
- feedback positivo dos turistas sobre facilidade de uso, clareza das informações e sensação de conhecer "mais a fundo" o destino;
- relatos de pequenos negócios e membros da comunidade a indicarem que passaram a receber mais contactos e visitantes graças à plataforma.

Estes indicadores ajudam a perceber, de forma simples, se a plataforma está de facto a **reduzir a falta de informação**, a **estimular um turismo menos superficial** e a **canalizar mais benefícios para dentro das comunidades locais**.

7. Riscos e Limitações

7.1. Falta de conteúdo real e atualizado

A plataforma depende de histórias, fotos, roteiros e perfis de negócios locais para ser útil. Se o conteúdo inicial for pouco ou ficar desatualizado (negócios que fecham, contactos que mudam), o utilizador pode perder confiança na solução. Além disso, recolher e manter esse conteúdo exige tempo, presença no terreno e colaboração com parceiros locais.

7.2. Baixa adesão de comunidades e pequenos negócios

Nem todas as comunidades ou empreendedores têm facilidade de acesso à internet, tempo disponível ou literacia digital para participar ativamente. Existe o risco de a plataforma ser usada apenas por quem já está mais "digitalizado", deixando de fora precisamente os atores mais marginalizados que o projeto quer incluir.

7.3. Complexidade técnica do modo offline-first

Garantir que mapas, roteiros e Story Stops podem ser descarregados, usados offline e atualizados mais tarde é tecnicamente desafiante. Se esta parte não for bem implementada, o aplicativo pode ficar pesado, lento ou com erros de sincronização, prejudicando a experiência do utilizador e a credibilidade da solução.

7.4. Escopo demasiado ambicioso para a equipa

A combinação de mapa, roteiros, Story Stops, gamificação, perfis de negócios e offline-first pode tornar o projeto demasiado grande para o tempo e recursos disponíveis. Há o risco de dispersão: várias funcionalidades incompletas em vez de um núcleo pequeno muito bem feito.

7.5. Diferença entre expectativas e realidade

Se na comunicação forem prometidos muitos destinos, funcionalidades avançadas ou impacto imediato nas comunidades, mas o protótipo entregue for ainda limitado, pode haver frustração por parte de utilizadores, parceiros ou avaliadores. É importante alinhar o discurso com o estado real do projeto (MVP/piloto).

7.6. Questões de responsabilidade e segurança

Ao sugerir roteiros e pontos de interesse, a plataforma assume alguma responsabilidade sobre a experiência do turista. Problemas como locais inseguros, serviços de má qualidade ou conflitos de expectativas podem gerar críticas e exigir mecanismos de aviso, filtragem e feedback.

8. Próximos Passos

8.1. Consolidação do MVP

Num primeiro momento, o foco será **consolidar o protótipo num MVP funcional**, com um conjunto mínimo de funcionalidades bem implementadas:

- seleção de um destino piloto;
- roteiros básicos (1 dia / 3 dias);
- alguns Story Stops representativos;
- registo simples de pontos/selos;
- funcionamento offline para estes conteúdos iniciais.

8.2. Piloto num destino específico

Depois do MVP, o passo seguinte é realizar um **teste piloto num destino real**, como a Ilha de Moçambique. Neste piloto, a equipa pretende:

- acompanhar turistas a usar a plataforma no terreno;
- recolher feedback sobre usabilidade, clareza da informação e utilidade dos roteiros;
- ouvir comunidades e pequenos negócios sobre a forma como estão representados.

8.3. Ajustes com base no feedback

Com os dados do piloto, serão feitas **melhorias iterativas**, por exemplo:

- simplificar ou reorganizar ecrãs;
- ajustar roteiros e Story Stops mais usados ou menos relevantes;
- melhorar mensagens, textos e ícones para evitar confusões.

8.4. Expansão gradual e parcerias

Numa etapa seguinte, o objetivo é **expandir para outros destinos turísticos** em Moçambique, de forma gradual, à medida que existam conteúdo e parceiros locais. Em paralelo, será importante procurar:

- parcerias com operadores turísticos, associações comunitárias e entidades públicas;
- oportunidades em competições, incubadoras ou programas de inovação em turismo para apoiar o desenvolvimento contínuo do projeto.

Conclusão

O projeto apresentado nasceu da vontade de melhorar a forma como Moçambique é descoberto por turistas e valorizado pelas próprias comunidades. Ao longo do trabalho, identificámos problemas claros: falta de informação estruturada no destino, pouca visibilidade de pequenos negócios locais, forte concentração do turismo em zonas "superficiais" e limitações de conectividade que tornam soluções 100% online pouco práticas. A partir deste diagnóstico, construímos a proposta de uma plataforma de turismo offline-first que funciona como um guia de bolso inteligente, desenhado para a realidade moçambicana.

A solução combina roteiros inteligentes, Story Stops com histórias locais, um sistema de gamificação e funcionamento offline, permitindo que turistas independentes explorem o país com mais autonomia, profundidade e segurança, ao mesmo tempo que dá palco a comunidades e empreendedores locais. O protótipo desenvolvido demonstrou que esta ideia é tecnicamente viável e foi bem recebida em contexto de competição, o que reforça o seu potencial. Ainda que existam riscos e limitações — desde a necessidade de conteúdo atualizado até à complexidade do offline-first — o plano de próximos passos mostra que há um caminho concreto para testar, melhorar e escalar a solução de forma gradual.

Em síntese, o projeto não é apenas um exercício académico ou tecnológico: é uma proposta prática para transformar o turismo em Moçambique num processo mais inclusivo, distribuído e conectado com o património imaterial do país. Com o desenvolvimento de um MVP, um piloto num destino específico e o envolvimento de parceiros locais, esta plataforma pode evoluir de protótipo para ferramenta real, contribuindo para que mais pessoas conheçam Moçambique para além da superfície e para que mais comunidades beneficiem diretamente do turismo.